00_Construccion_grafo

April 10, 2026

1 Reporte 00: Construcción del Grafo Topológico (Modelo VFT)

1.1 1. Justificación Teórica: Del GeoJSON al Grafo Matemático

En el análisis de redes de transporte urbano, un mapa estático (polígonos y líneas) es insuficiente para modelar el comportamiento operativo. El **Modelo Vanishing Fig-Tree (VFT)** requiere transformar las geometrías espaciales extraídas de la APIMETRO (en formato GeoJSON) en una estructura matemática conocida como **Grafo Dirigido**.

Matemáticamente, definimos la red topológica como:

$$G = (V, E)$$

Donde: * V **(Vértices o Nodos):** Representan las estaciones del sistema. Sus atributos incluyen las coordenadas espaciales estáticas (longitud, latitud) y su jerarquía operativa (ej. "masivo_pesado", "superficie_convencional"). * E **(Aristas o Edges):** Representan los vectores de flujo continuo entre dos vértices adyacentes ($\vec{uv}$). Cada arista posee atributos dinámicos cruciales, principalmente la **Impedancia Temporal**, la cual está condicionada por el coeficiente de fricción vial, el derecho de vía y la velocidad comercial del sistema.

Esta transformación espacial nos permite aplicar algoritmos de enrutamiento y evaluar la resiliencia y accesibilidad del sistema anillar de la Ciudad de México.

```
1. Conectando con APIMETRO (Go) para ingestar la red espacial…
2026-04-09 23:50:02 | INFO     | VFT_Model | Construyendo el puente hacia el
módulo espacial de Go…
2026-04-09 23:50:02 | INFO     | VFT_Model | Solicitando capa espacial a:
http://localhost:8080/movilidad/mapas/geojsonEstacion
2026-04-09 23:50:02 | INFO     | VFT_Model | Solicitando capa espacial a:
http://localhost:8080/movilidad/mapas/geojsonLinea
2026-04-09 23:50:02 | INFO     | VFT_Model | Red extraída: 22785 entidades
espaciales listas para VFT.
2. Validando contrato de datos espaciales (Pydantic)…
  Ingesta exitosa: Se validaron 22785 features espaciales.
```

1.2 2. Renderizado del Grafo VFT: Construcción Paso a Paso

Para comprender cómo el **Modelo VFT** procesa la geometría espacial y la transforma en una estructura matemática operativa, a continuación se desglosa la construcción de la red topológica en cuatro etapas analíticas.

```
2026-04-09 23:50:14 | INFO     | VFT_Model | Iniciando VFTGraphBuilder en modo:
REALISTIC_INTEGRATION
2026-04-09 23:50:14 | INFO     | VFT_Model | Fase 1 y 2: Extrayendo nodos y
trazos base…
2026-04-09 23:50:15 | INFO     | VFT_Model | Grafo Base construido: 101621 Nodos
y 93816 Segmentos.
2026-04-09 23:50:15 | INFO     | VFT_Model | Fase 3: Integrando sistemas
(Tolerancia peatonal: 85.0m)…
2026-04-09 23:50:40 | INFO     | VFT_Model | Se crearon 20482 aristas de
Transbordo Peatonal.
2026-04-09 23:50:40 | INFO     | VFT_Model | Aplicando Motor de Impedancia…
2026-04-09 23:50:40 | INFO     | VFT_Model | Iniciando inyección de motor de
impendancia sobre VFT:
2026-04-09 23:50:41 | INFO     | VFT_Model | Impedancia aplicada exitosamente a
114298 segmentos.
 Grafo topológico construido exitosamente: 101621 nodos y 114298 aristas.
```

1.2.1 Etapa 1: Vértices Topológicos y Jerarquía del Sistema (V)

El primer paso consiste en mapear estrictamente las estaciones como vértices. El tamaño y color de cada nodo representan su **jerarquía de transporte** (Masivo Pesado, Mediano o Superficie Convencional). Esta es la base esquelética donde interactúan los transbordos.

```
2026-04-09 23:50:41 | INFO     | VFT_Model | Visualizador inicializado. Pre-
procesando geometrías…
2026-04-09 23:50:41 | INFO     | VFT_Model | Renderizando paneles solicitados:
All=1
2026-04-09 23:50:42 | INFO     | VFT_Model | Visualización guardada exitosamente
en: ASSETS/00_Panel1_Nodos_Jerarquia.png
```

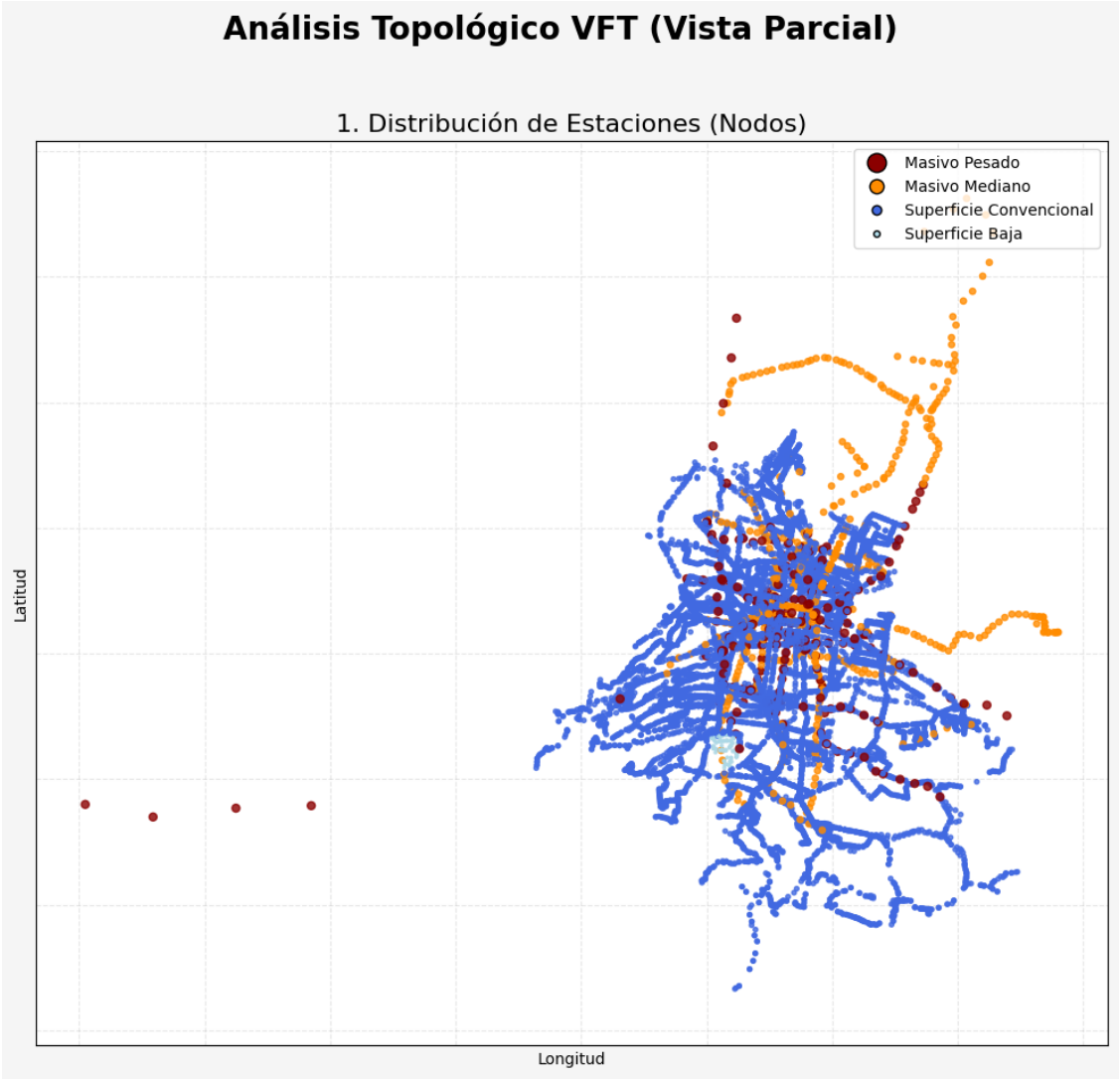

1.2.2 Etapa 2: Arcos y Topología Espacial (E)

A continuación, se trazan los segmentos de conexión física. La red pasa de ser un conjunto aislado de puntos a un **grafo continuo**. El grosor y color de los arcos mapean características vitales como el derecho de vía y la velocidad comercial.

```
2026-04-09 23:50:42 | INFO     | VFT_Model | Visualizador inicializado. Pre-
procesando geometrías…
2026-04-09 23:50:42 | INFO     | VFT_Model | Renderizando paneles solicitados:
All=2
2026-04-09 23:50:43 | INFO     | VFT_Model | Visualización guardada exitosamente
en: ASSETS/00_Panel2_Arcos_Espaciales.png
```

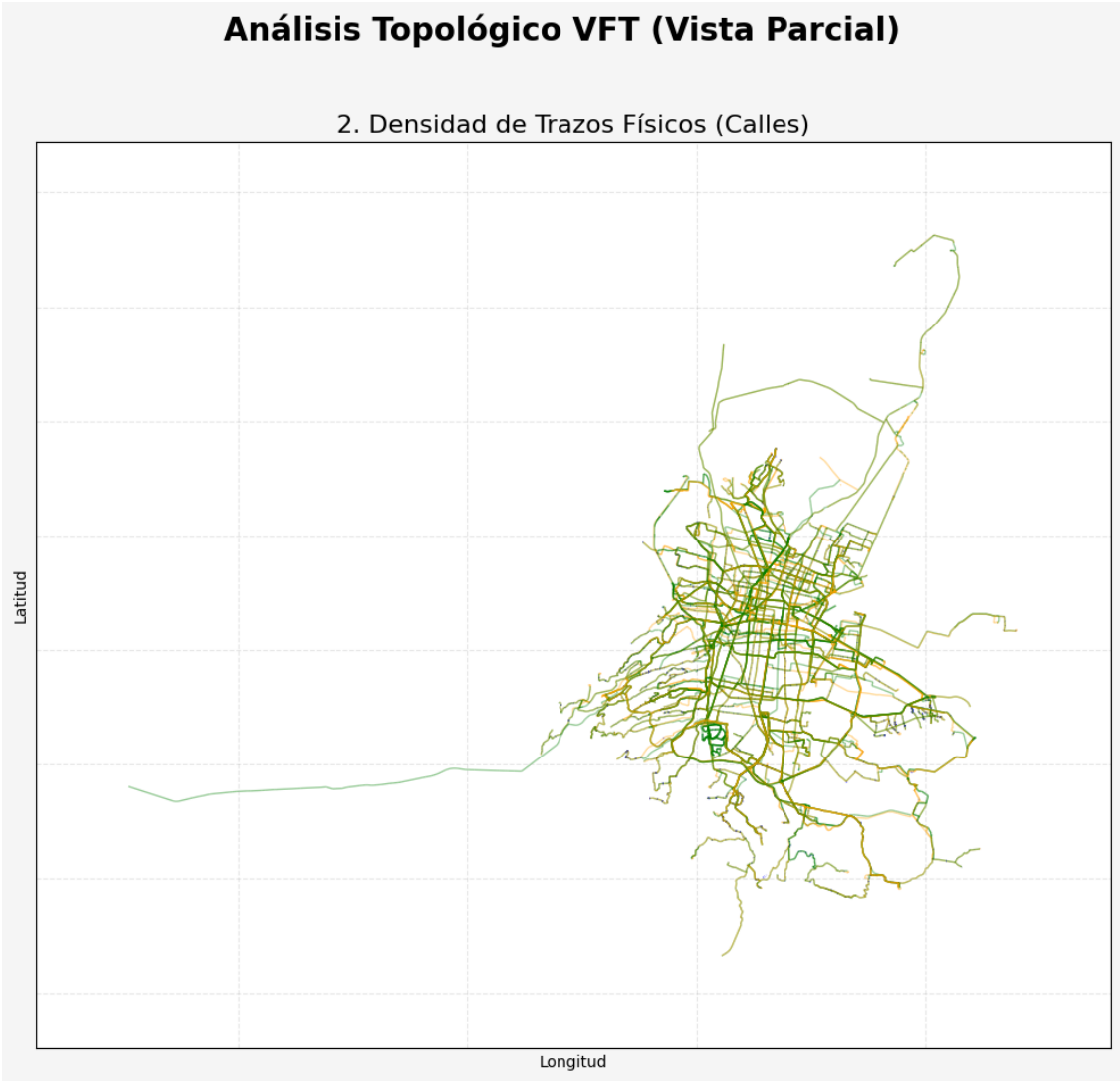

1.2.3 Etapa 3: Direccionalidad Operativa (Flujos de Ida)

Al ser un Grafo Dirigido (DiGraph), la red no es simétrica. Aquí visualizamos los vectores de flujo continuo en su sentido de operación principal (Ida). Esta asimetría es crucial para que el Motor de Impedancia calcule el verdadero costo de viaje temporal.

```
2026-04-09 23:50:44 | INFO     | VFT_Model | Visualizador inicializado. Pre-
procesando geometrías…
2026-04-09 23:50:44 | INFO     | VFT_Model | Renderizando paneles solicitados:
All=3
2026-04-09 23:51:24 | INFO     | VFT_Model | Visualización guardada exitosamente
en: ASSETS/00_Panel3_Flujos_Ida.png
```

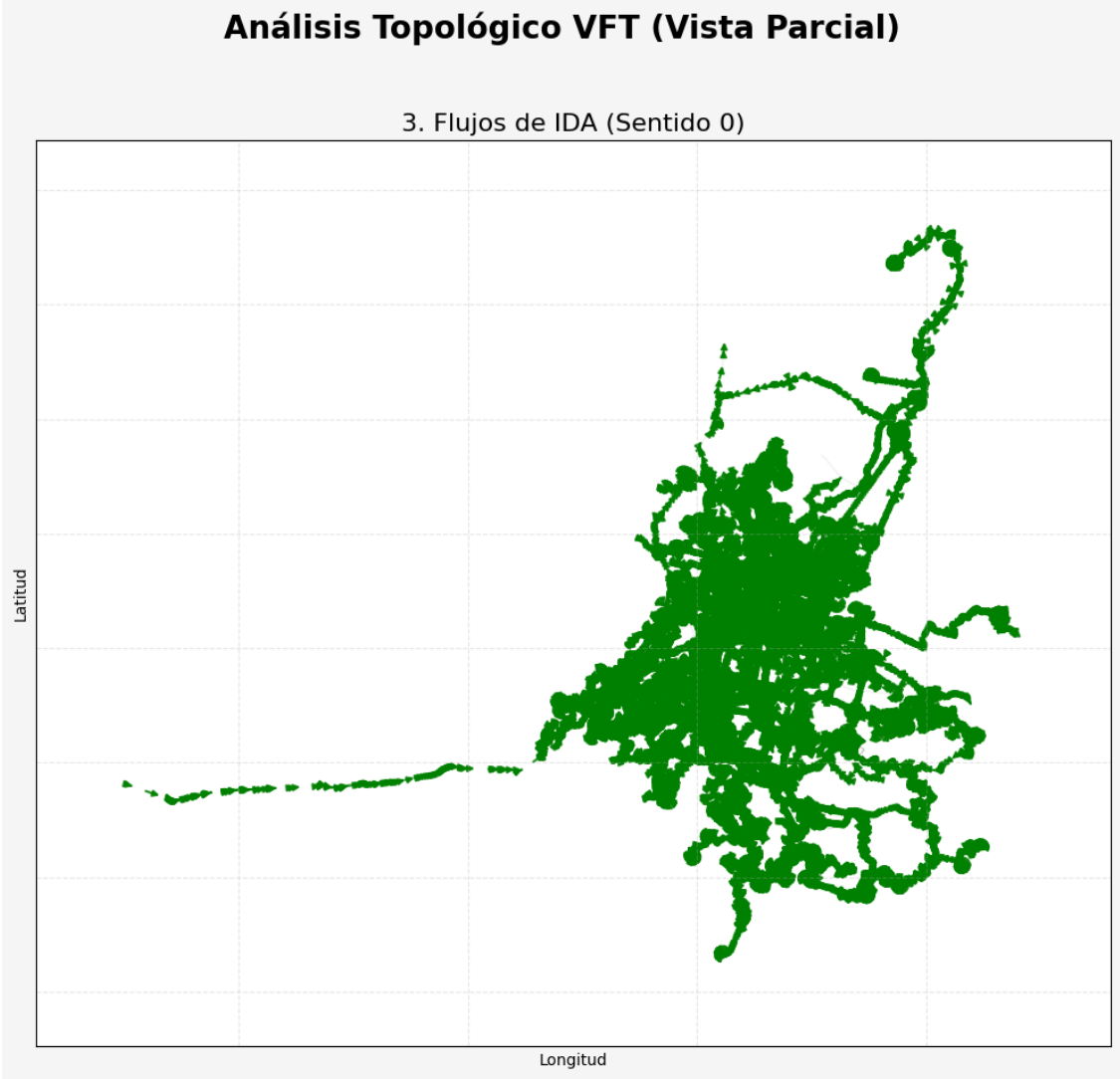

1.2.4 Etapa 4: Direccionalidad Operativa (Flujos de Regreso)

Finalmente, se mapean las aristas en sentido inverso. Al contrastarse con el flujo de ida, el modelo es capaz de identificar discrepancias viales, cuellos de botella y evaluar la resiliencia bidireccional del sistema completo.

```
2026-04-09 23:51:35 | INFO     | VFT_Model | Visualizador inicializado. Pre-
procesando geometrías…
2026-04-09 23:51:35 | INFO     | VFT_Model | Renderizando paneles solicitados:
All=4
2026-04-09 23:52:15 | INFO     | VFT_Model | Visualización guardada exitosamente
en: ASSETS/00_Panel4_Flujos_Regreso.png
```

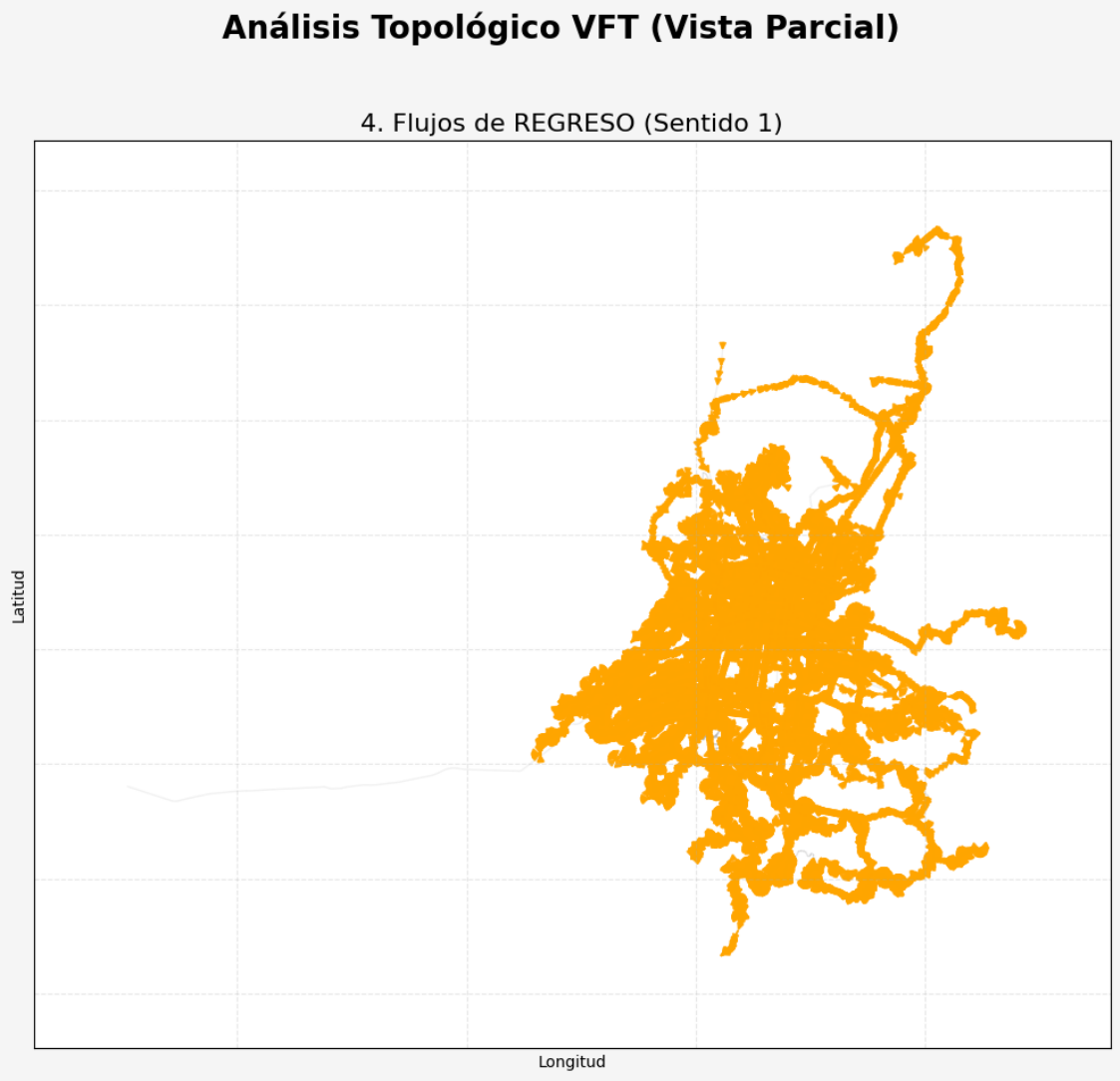
Análisis Topológico VFT (Vista Parcial)
4. Flujos de REGRESO (Sentido 1)
Latitud
Longitud