03_Fuerza_capilar

April 8, 2026

1 Reporte 03: Fuerza Capilar (Grado Nodal) y Nodos de Transferencia Intermodal (FC)

1.1 1. Justificación Teórica

El presente indicador evalúa la **Fuerza Capilar** de la red de transporte, definida topológicamente como el grado nodal (k) de cada estación. Este indicador cuantifica el nivel de convergencia de flujos y la capacidad de un nodo para actuar como punto de transferencia intermodal.

Para obtener una radiografía urbana realista y mitigar la inflación geométrica, el modelo divide la Fuerza Capilar en dos dimensiones analíticas:

A. Fuerza Capilar Geográfica (Macro-Hubs): Agrupa topológicamente estaciones físicamente colindantes (radio de tolerancia de 100m) en un subgrafo H. Consolida los flujos de sus estaciones constituyentes eliminando las duplicidades. Representa el fenómeno urbano del transbordo físico (ej. CETRAMs):

$$FC_H = \sum_{j \in H} (k_{in}(j) + k_{out}(j)) - \text{Aristas Internas}$$

B. Fuerza Capilar Matemática / Estricta (Por Estación Individual): Calcula el grado de entrada y salida de un nodo topológico i, aplicando un filtro de frontera espacial (radio de 25m) para capturar únicamente los vectores de flujo. Representa la centralidad pura del nodo en el grafo:

$$FC_i = k_{in}(i)_{frontera} + k_{out}(i)_{frontera}$$

```
The autoreload extension is already loaded. To reload it, use:
  %reload_ext autoreload
```

```
 Descargando red de transporte…
2026-04-08 17:25:12 | INFO     | VFT_Model | Construyendo el puente hacia el
módulo espacial de Go…
2026-04-08 17:25:12 | INFO     | VFT_Model | Solicitando capa espacial a:
http://localhost:8080/movilidad/mapas/geojsonEstacion
2026-04-08 17:25:12 | INFO     | VFT_Model | Solicitando capa espacial a:
http://localhost:8080/movilidad/mapas/geojsonLinea
2026-04-08 17:25:12 | INFO     | VFT_Model | Red extraída: 22785 entidades
espaciales listas para VFT.
 Construyendo Grafo Dirigido VFT…
```

```
2026-04-08 17:25:12 | INFO     | VFT_Model | Iniciando la construcción del Grafo
VFT…
2026-04-08 17:25:13 | INFO     | VFT_Model | Grafo Dirigido construido: 101621
Nodos topológicos y 93816 Segmentos de flujo.
2026-04-08 17:25:13 | INFO     | VFT_Model | Llamando al Motor de Impedancia
VFT…
2026-04-08 17:25:13 | INFO     | VFT_Model | Iniciando inyección de motor de
impendancia sobre VFT:
2026-04-08 17:25:13 | INFO     | VFT_Model | Impedancia aplicada exitosamente a
93816 segmentos.
 Grafo construido: 101621 nodos topológicos.
```

1.2 4. Ejecución del Motor Topológico

A continuación, instanciamos el analizador sobre el grafo dirigido (`G`) y calculamos ambos escenarios de fuerza capilar.

```
Nodos individuales procesados: 11115
Macro-Hubs consolidados: 3800
```

1.3 5. Análisis Geográfico: Macro-Hubs Intermodales

Este enfoque revela la infraestructura física de transbordo. Al agrupar estaciones cercanas, emergen los grandes polígonos de movilidad de la ciudad.

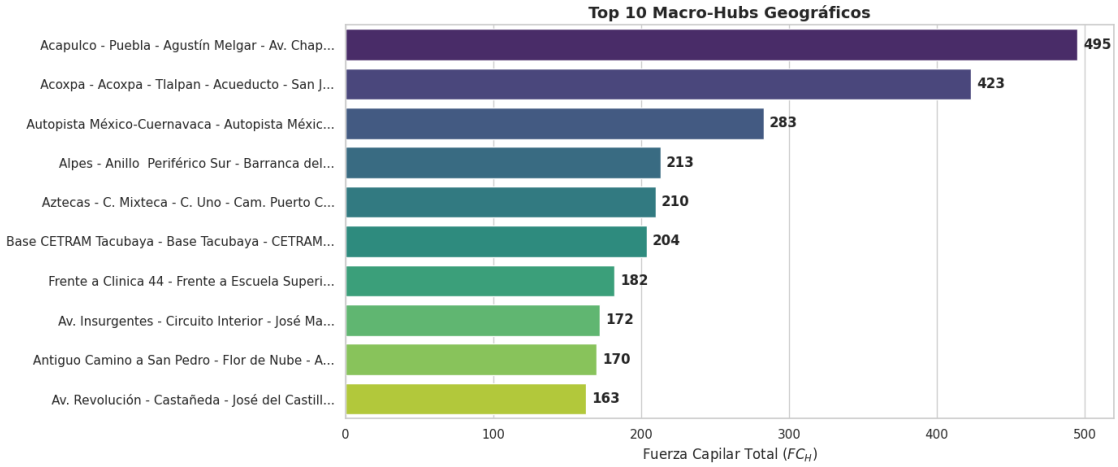


```
<folium.folium.Map at 0x79463e5494c0>
```

1.4 6. Análisis Matemático: Centralidad Estricta

Evalúa la convergencia puntual sin agrupaciones, detectando puntos específicos (coordenadas únicas) que soportan una gran carga de vectores vehiculares.

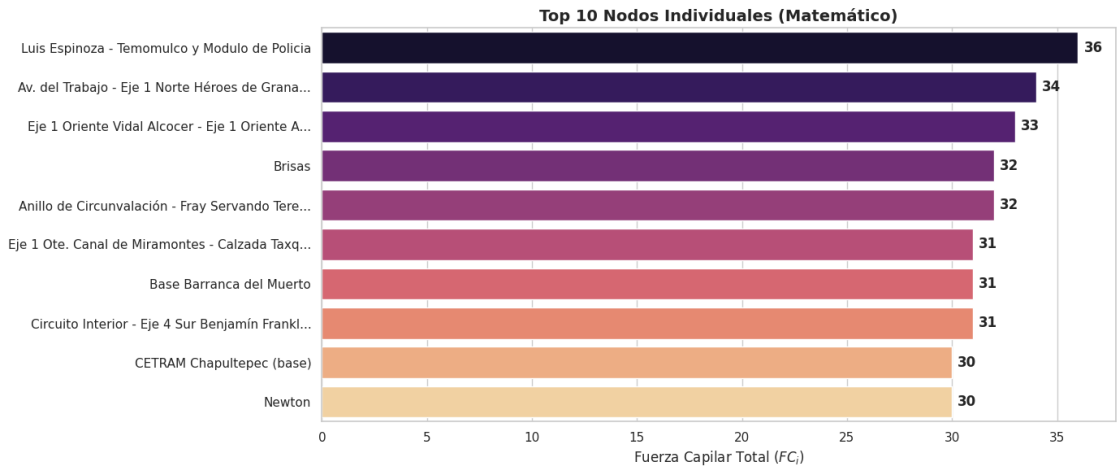


```
<folium.folium.Map at 0x79463e46f1a0>
```

1.4.1 6.1. Distribución de la Capilaridad Matemática (Ley de Potencias)

La topología de la red sigue una distribución de **Scale-Free Network** (Ley de Potencias). ¿Por qué ocurre esto? En los sistemas de transporte reales, la inmensa mayoría de las paradas actúan como nodos de paso simples (1 conexión de entrada y 1 de salida = FC de 2). Por el contrario, un grupo extremadamente reducido de nodos actúa como absorbedores masivos de rutas (decenas de conexiones). Esta desigualdad genera la curva logarítmica descendente que vemos a continuación.

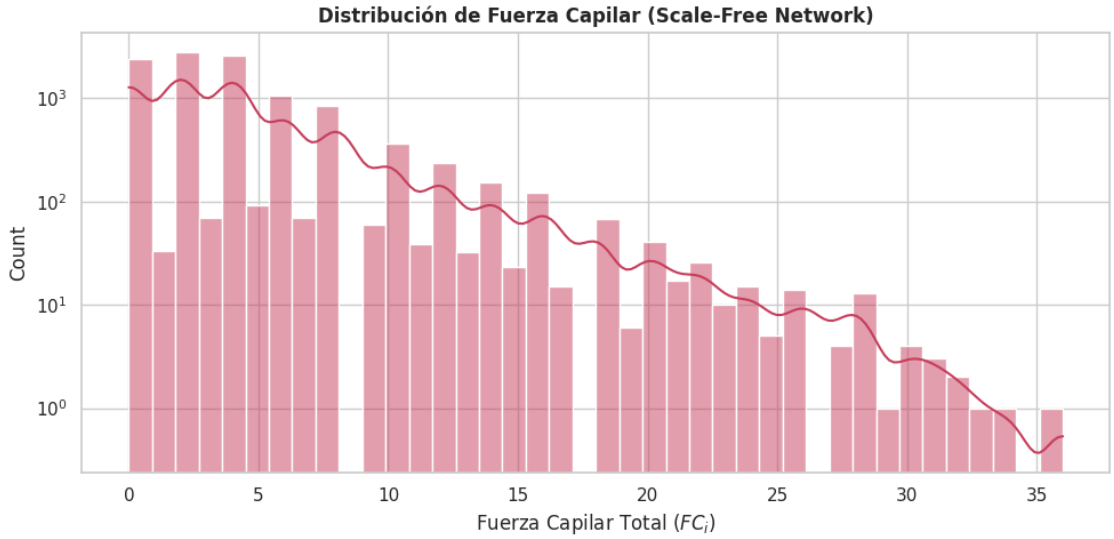

```
Ejemplo de la polarización en la red:

                                                Estacion Sistemas_Integrados  \
7264      Luis Espinoza - Temomulco y Modulo de Policia                [RTP]
1257  Av. del Trabajo - Eje 1 Norte Héroes de Granad…               [RTP]
6466                                     Ignacio Allende                [RTP]
6402           Honorable Congreso de la Unión - Platino                [RTP]

      Fuerza_Capilar_Total
7264                    36
1257                    34
6466                     2
6402                     2
```

1.5 7. Anexo: Diagnóstico Especulativo para Ruta Anillar (Periférico)

Este apartado aísla los nodos y Macro-Hubs que cruzan o se nombran "Periférico". Se divide en la perspectiva Matemática y Geográfica para identificar anclajes potenciales.

1.5.1 7.1. Eje Periférico: Perspectiva Geográfica (Macro-Hubs)

Muestra los polígonos de transferencia más fuertes a lo largo de la vialidad.

```
Ejemplo de Estaciones Periféricas en la Red Geográfica:

                                            Macro_Hub  \
 227  Alpes - Anillo  Periférico Sur - Barranca del …
 345  Anillo Periférico Canal de Garay - Constitució…
 293  Anillo Periférico - Anillo Periférico Sur - Al…
 945  Av. San Lorenzo - Av. Tláhuac - Av. Tláhuac - …
 306  Anillo Periférico Blvd. Adolfo Ruiz Cortines -…

                              Sistemas_Integrados  \
 227                   [CORREDOR_CONCESIONADO, RTP]
 345         [CORREDOR_CONCESIONADO, METROBUS, RTP]
 293                   [CORREDOR_CONCESIONADO, RTP]
 945  [CORREDOR_CONCESIONADO, METRO, RTP, TROLEBUS]
 306                   [CORREDOR_CONCESIONADO, RTP]

                                  Detalle_Estaciones  Estaciones_Agrupadas  \
 227  {'CORREDOR_CONCESIONADO': ['Alpes', 'Av. Revol…                    21
 345  {'RTP': ['Anillo Periférico Canal de Garay - C…                     8
 293  {'RTP': ['Anillo Periférico', 'Anillo Periféri…                    10
 945  {'RTP': ['Av. Tláhuac', 'Av. Tláhuac - Anillo …                     9
 306  {'RTP': ['Anillo Periférico Blvd. Adolfo Ruiz …                     9
```

```
     Conexiones_Entrada  Conexiones_Salida  Fuerza_Capilar_Total
227                 106                107                   213
345                  59                 59                   118
293                  54                 54                   108
945                  38                 38                    76
306                  32                 32                    64
```

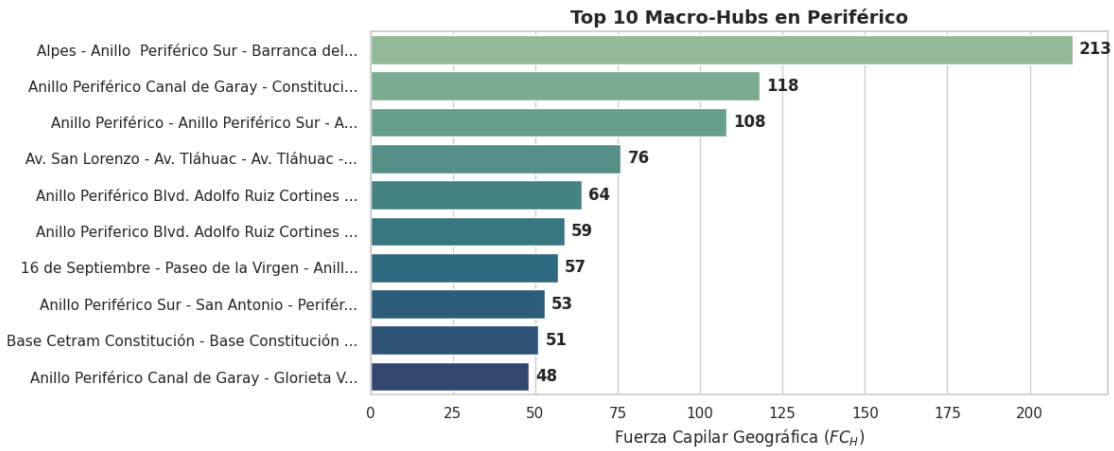


```
<folium.folium.Map at 0x7946386963c0>
```

1.5.2 7.2. Eje Periférico: Perspectiva Matemática (Nodos Individuales)

Muestra las coordenadas exactas de mayor tensión vehicular intermodal sobre el anillo.

```
                    Nodo_ID                                     Estacion  \
8538  (-99.19147, 19.36391)              Periférico - Barranca del Muerto
509   (-99.19096, 19.36316)  Anillo  Periférico Sur - Barranca del Muerto
690   (-99.19144, 19.36385)   Anillo Periférico Sur - Barranca del Muerto
6527  (-99.21615, 19.44177)         Industria Militar - Anillo Periférico
8692   (-99.1585, 19.52746)                              Periférico Norte

          Sistemas_Integrados  \
8538  [CORREDOR_CONCESIONADO]
509                     [RTP]
690                     [RTP]
6527  [CORREDOR_CONCESIONADO]
8692                    [RTP]

                                  Detalle_Estaciones  Estaciones_Agrupadas  \
8538  {'CORREDOR_CONCESIONADO': ['Periférico - Barra…                     1
509   {'RTP': ['Anillo  Periférico Sur - Barranca de…                     1
690   {'RTP': ['Anillo Periférico Sur - Barranca del…                     1
```

```
6527  {'CORREDOR_CONCESIONADO': ['Industria Militar …                    1
8692                      {'RTP': ['Periférico Norte']}                    1

      Conexiones_Entrada  Conexiones_Salida  Fuerza_Capilar_Total
8538                  11                 11                    22
509                   11                 11                    22
690                   11                 11                    22
6527                  10                 10                    20
8692                  10                 10                    20
```

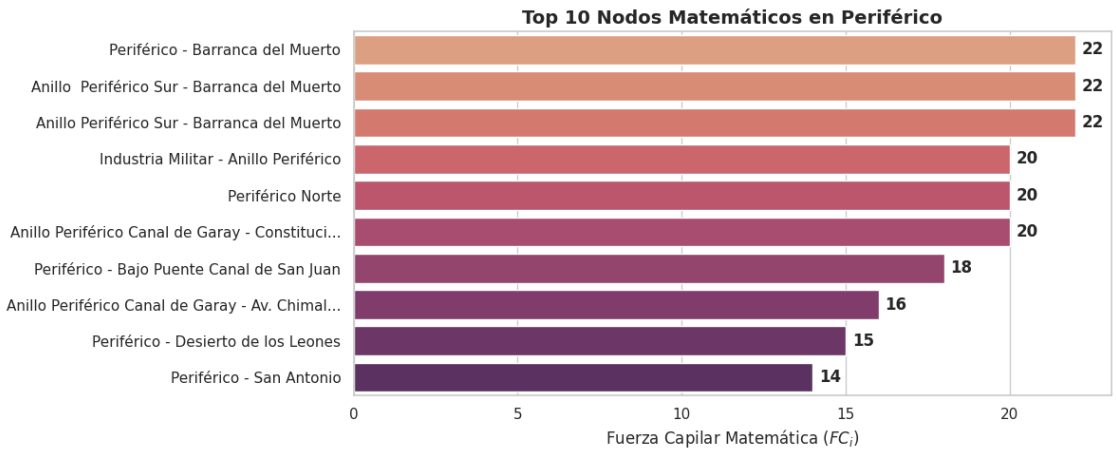


```
<folium.folium.Map at 0x79463f2f9520>
```

Nota Aclaratoria: *Los mapas mostrados en la Sección 7 representan únicamente una evaluación de la infraestructura preexistente. Aún no se traza ni se mapea el recorrido geométrico propuesto para el "Corredor Anillar", por lo que esta sección se mantiene en un plano puramente especulativo para identificar los puntos naturales de anclaje de la futura línea.*